PORTFOLIO

Daniela Rodríguez

Dashboards enfocados en análisis y toma de decisiones.

CADENA DE SUMINISTROS

Air | Rail | Road | Sea

Productos Totales
100

Gastos Totales
52,92 mil

Tiempo de Manufactura
15

INSPECCIÓN DE LOS PRODUCTOS

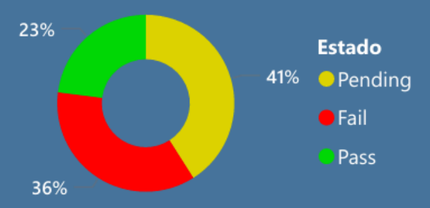

SKU_pk	Suma de Stock levels	Suma de Production volumes	Suma de Order quantities
12	100	563	85
51	100	673	52
59	100	176	26
91	98	207	85

COSTO TOTAL POR TIPO DE PRODUCTO Y LUGAR

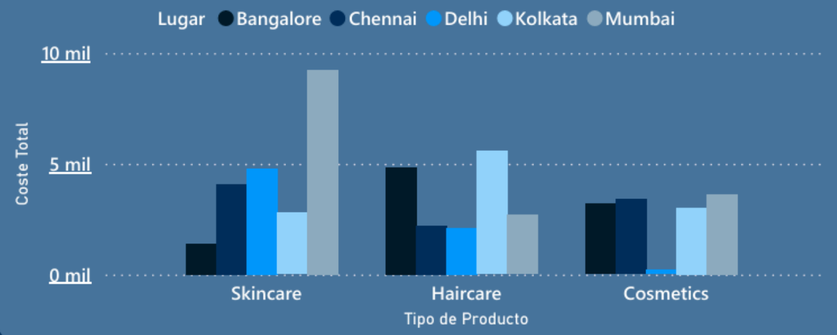

CANTIDAD DE PRODUCTO POR PROVEEDOR

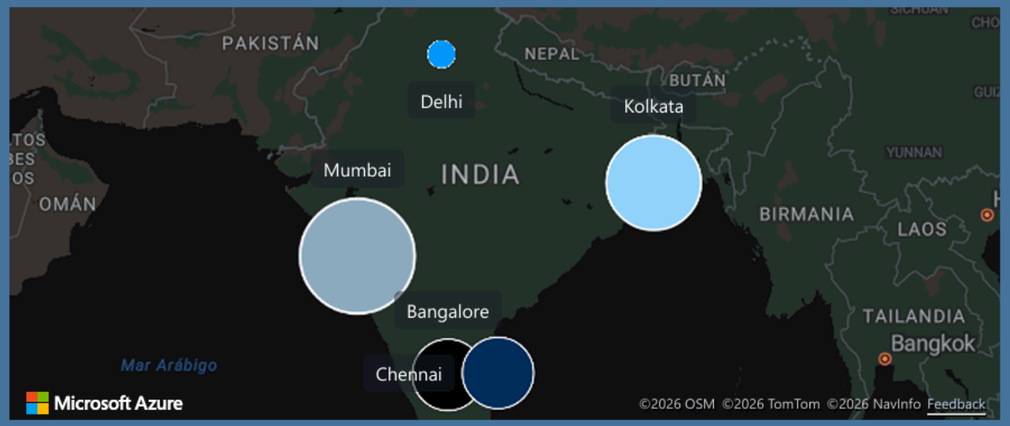

ANÁLISIS Y CONCLUSIÓN

La cadena de suministros cuenta con 100 productos, un coste operativo cercano a 53 mil y un tiempo de manufactura promedio de 15 días. Las inspecciones muestran problemas de calidad, con solo 23% de productos aprobados y altos porcentajes de fallos y pendientes. También hay un desbalance entre inventario, producción y demanda, con riesgo de no cubrir la demanda y sobreproducción en otros. La operación depende en gran medida de proveedores en Mumbai y Kolkata, y los costos varían notablemente por ubicación, especialmente en skincare transportado por vía aérea. Todo ello señala oportunidades claras para optimizar proveedores, inventarios y costos.

Proyecto Grupal - Permite seguir la salud del talento y la experiencia del empleado: muestra el NPS interno, resultados de encuesta 360 y desarrollo por departamento, además de la evolución de bajas de empleados para detectar tendencias de rotación/abandono, áreas con mayor riesgo y priorizar acciones de clima, formación y retención.

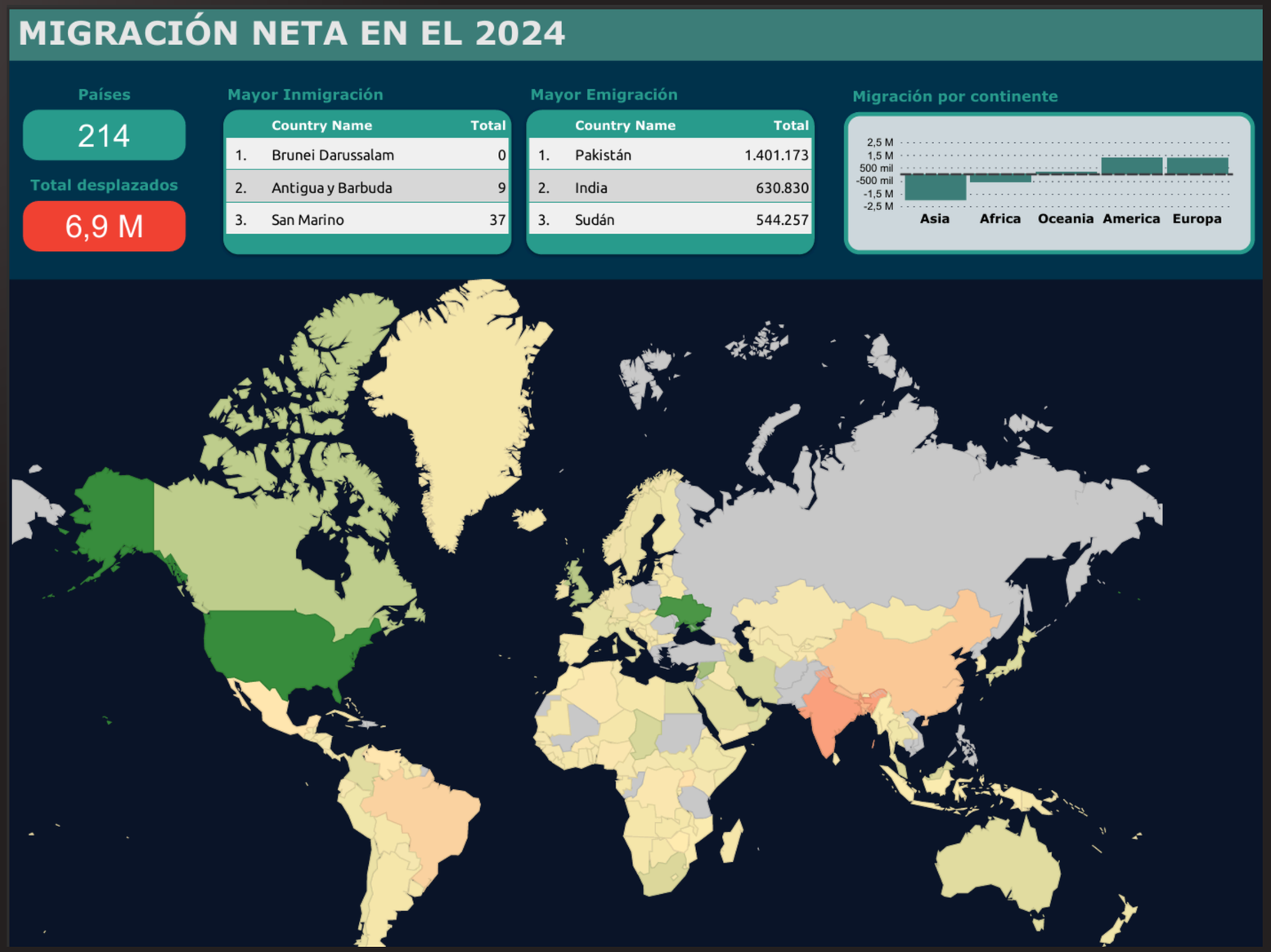

Este dashboard sirve para ver rápido la migración neta en 2024: cuántos desplazados hay (6,9M) y cuántos países incluye (214). También muestra qué países tienen más inmigración y cuáles más emigración, compara la migración por continente y en el mapa se ve dónde se concentran los flujos. Es útil para analistas, ONGs o instituciones que quieran detectar tendencias y focos principales para orientar recursos, políticas o investigaciones.

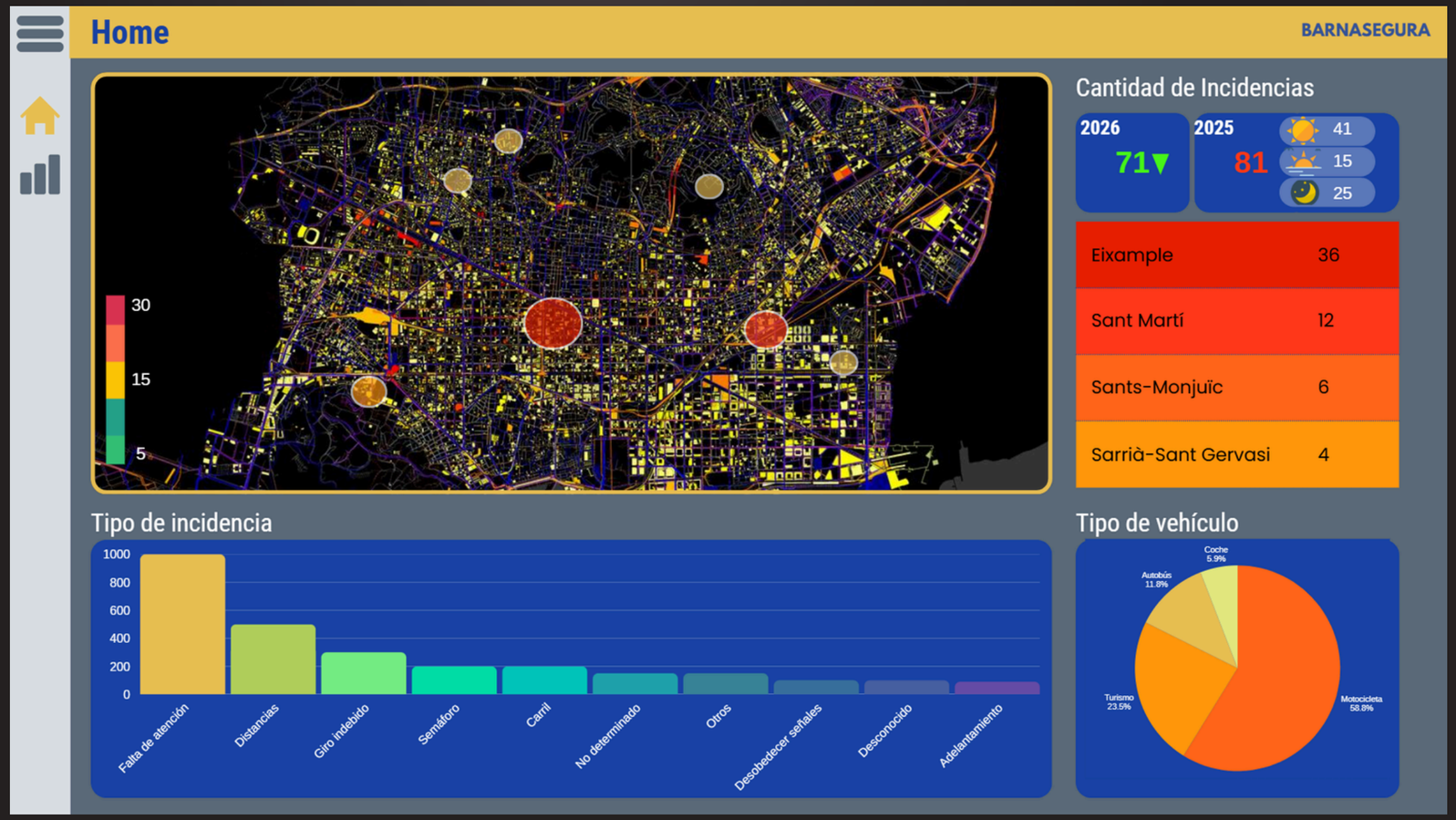

Este dashboard sirve para ver rápido las incidencias de tráfico en Barcelona: en el mapa se ve dónde se concentran los puntos con más incidentes, y a la derecha se compara la cantidad de incidencias por año y por distrito/zona. Abajo muestra el tipo de incidencia (para saber qué es lo más común) y el tipo de vehículo involucrado. En general, ayuda a detectar zonas críticas y qué problemas se repiten para priorizar medidas de seguridad y control.

GRACIAS